النشاط المقترح : مجمع خدمات لوجيستي

1 بيانات الموقع

المنطقة	الحدود الشمالية	المدينة	عرعر
الحي	حزم الجلاميد	رقم القطعة	ت7+ت9+ت11
المساحة	(19,656.75+ 20,839.68+ 20,831.68) M2	رقم المخطط	1432/د/ر/22 المعدل
رابط الوصول	https://maps.app.goo.gl/wuE72tBg2RRqu4wG8		

2 البيانات المكانية

الوصول للموقع

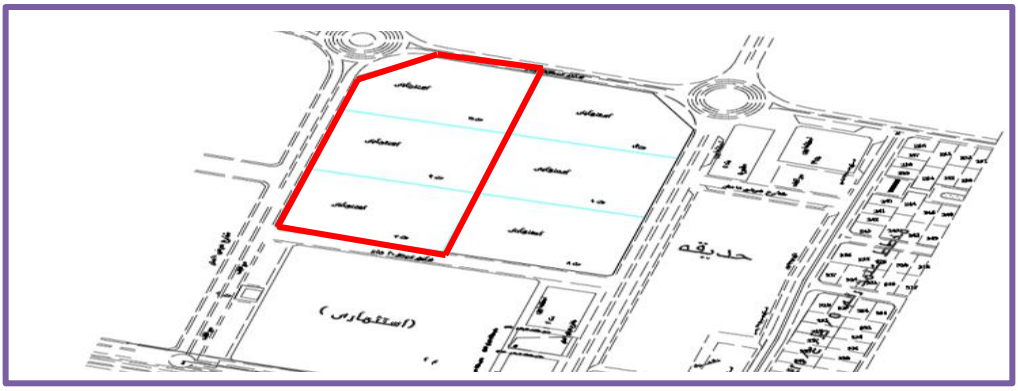

الموقع التفصيلي

ت7

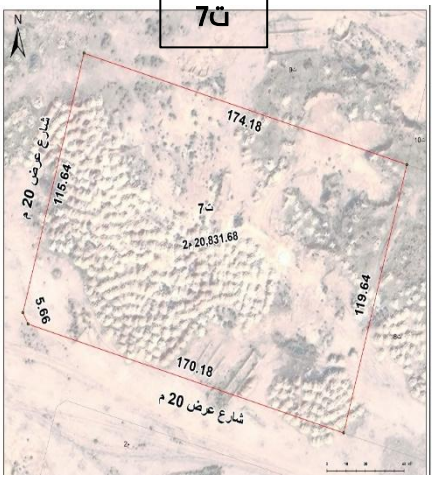

النقطة	الشرقيات	الشماليات
p1	604305.8026	3461765.336
p2	604273.0036	3461650.277
p3	604109.3421	3461696.93
p4	604106.5914	3461701.875
p5	604138.2936	3461813.087

ت9

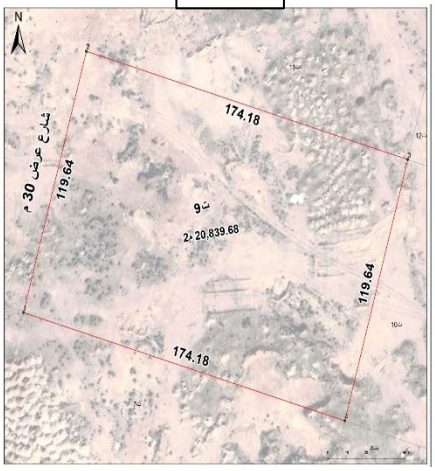

النقطة	الشرقيات	الشماليات
p1	604138.2936	3461813.087
p2	604171.0925	3461928.146
p3	604338.6016	3461880.396
p4	604305.8026	3461765.336

ت11

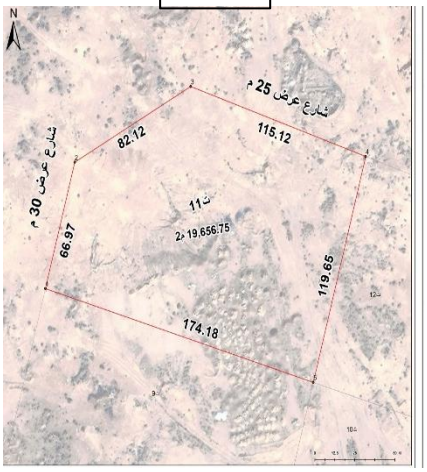

النقطة	الشرقيات	الشماليات
p1	604171.0925	3461928.146
p2	604189.4519	3461992.551
p3	604261.9429	3462031.128
p4	604371.4013	3461995.458
p5	604338.6016	3461880.396